Lost Dog Tracer

Benutzer Handbuch

Einleitung

Lost Dog Tracer ist eine Web App zur Unterstützung bei der Suche nach entlaufenen Hunden. Der Hauptzweck besteht darin, verschiedenste Standort Informationen zu Sichtungen, Flyer Aktionen, Futterstellen, Fallen etc. an einer zentralen Stelle zu sammeln und bereitzustellen.

Insbesondere bei Flyer Aktionen kommen schnell dutzende Standorte zusammen. Hier ist es besonders wichtig ein einfaches zu bedienendes, schnelles Werkzeug zu Erfassung dieser Standorte zu haben. Dies war die Grundidee von Lost Dog Tracer. Mittlerweile wurde die App weiter ausgebaut und bei Bedarf auch weiter entwickelt.

Dieses Handbuch erklärt die erweiterten Funktionen der App. Bitte lies zuvor die Einführen in „Lost Dog Tracer - 1 - Einrichtung und erste Schritte“.

Hinweise zu bekannten Problemen und deren Lösung finden sich ebenfalls in „Lost Dog Tracer - 1 - Einrichtung und erste Schritte“.

Lost Dog Tracer steht als Open Source unter der MIT / Expat Lizenz zur freien Verfügung.

Inhalt

Einleitung 1

1. Funktionsübersicht 3

2. GPS-Daten 4

2.1 Neuen Eintrag aus Adresse erstellen 5

2.2 Daten Bearbeiten 7

2.3 Kartenansicht 8

3. Hunde Verwaltung 10

3.1 Gast Zugang 11

4. Benutzer Verwaltung (eingeschränkt) 12

1. Funktionsübersicht

Lost Dog Tracer ist eine Web App, welche für die Nutzung mit Smartphones optimiert wurde. **Dennoch wird für die erweiterten Funktionen die Nutzung eines PC/Mac oder Tablett empfohlen**. Die Arbeit mit Tabellen und Karten ist hier deutlich einfacher.

Folgende Funktionen stehen, abhängig von der Rolle des Benutzers, zur Verfügung:

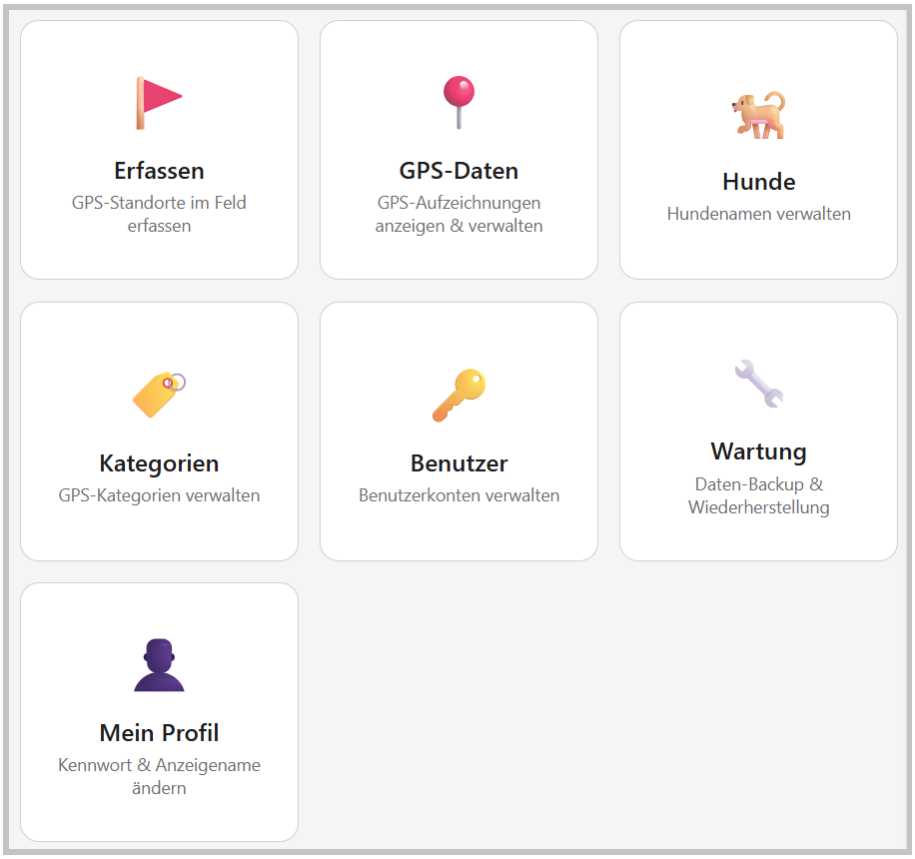

Rolle	Level	Zugriff
User	1	Erfassen, Mein Profil
PowerUser	2	+ GPS-Daten (lesen, bearbeiten, löschen)
Manager	3	+ Hunde, Benutzer (anlegen, nur Rolle "User")
Administrator	4	+ Kategorien, Wartung, Benutzer bearbeiten/löschen/Kennwort, alle Rollen vergeben

2. GPS-Daten

Diese Funktion ist das funktionale Zentrum der App. Es stehen umfangreichen Möglichkeiten zur grafischem Darstellung auf Karten sowie Filtermöglichkeiten zur Verfügung. Zudem können Standort Daten nachgepflegt werden, ohne selbst am Ort sein zu müssen. Z.B. bei Sichtungen oder dem Ort des Entlaufens.

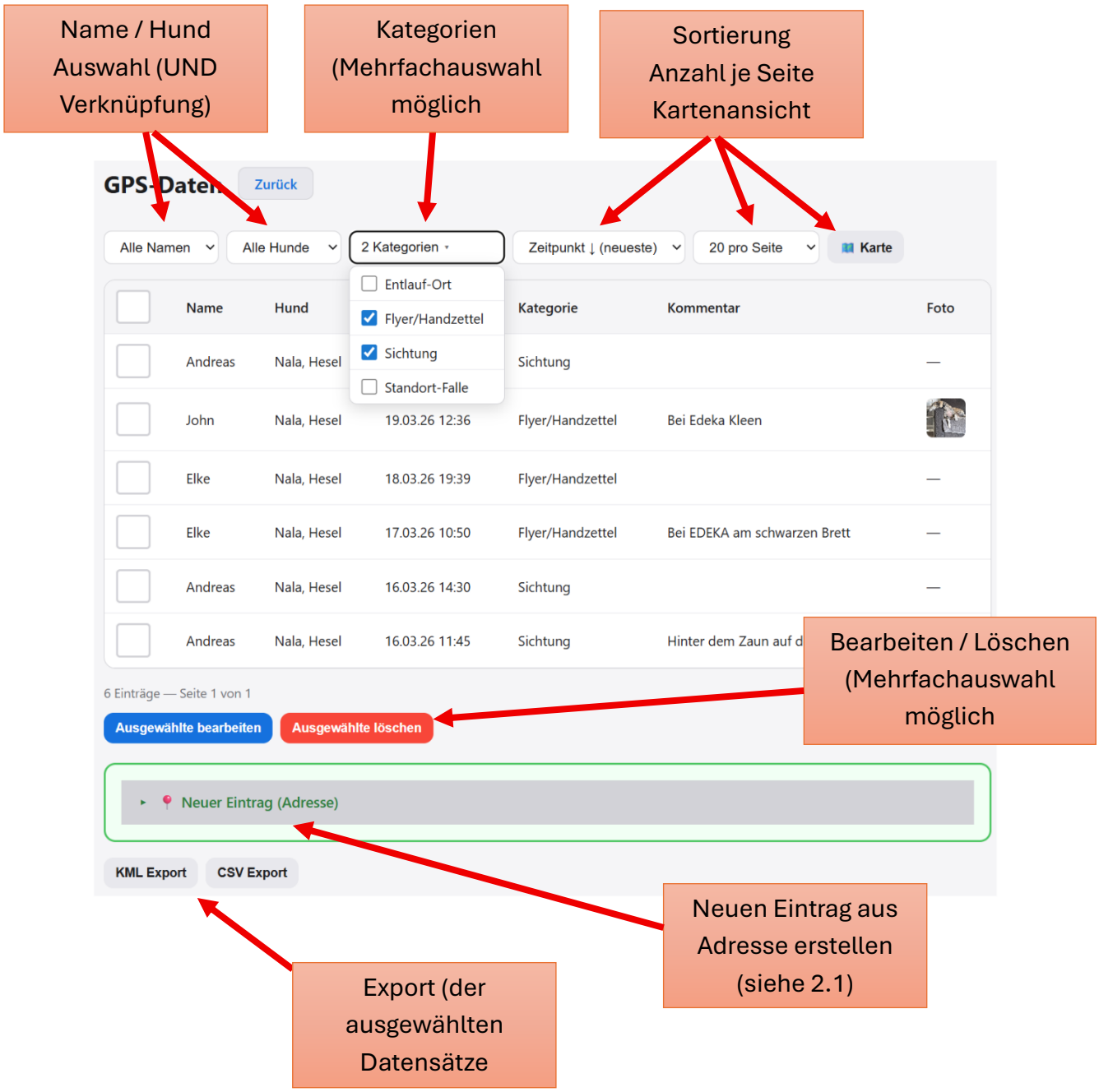

2.1 Neuen Eintrag aus Adresse erstellen

Insbesondere bei Sichtungen oder dem Ort des Entlaufen ist der Helfer nicht vor Ort. Mit dieser Funktion können diese Standorte nachgepflegt werden.

Wichtig: Soll z.B. bei Sichtungen die Bewegung des Hundes grafisch dargestellt werden müssen die Zeitangaben korrekt eingegeben werden!

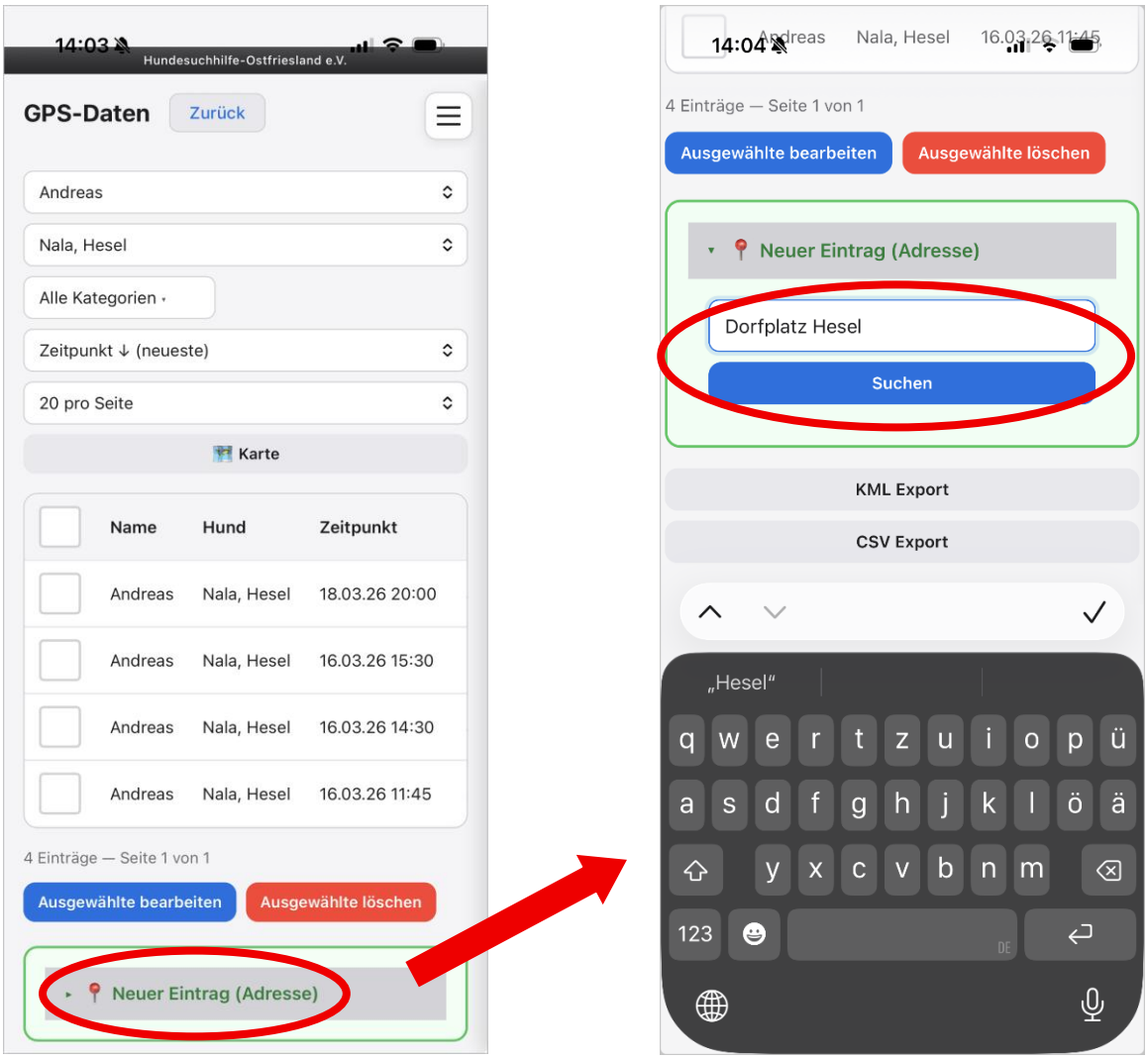

Im Suchfeld können, wie bei gängigen Karten- oder Navigationsapps, Suchbegriffe eingegeben werden. Eine vollständige Adresse ist auch möglich, aber nicht notwendig.

Wenn die Adresse gefunden wurde kann sie übernommen werden. Ein Kartenmarker wird automatisch angezeigt. Der Marker kann frei verschoben und platziert werden.

Hinweis: Die App speichert <u>nicht</u> die Adresse, sondern die GPS Koordinaten des Marker!

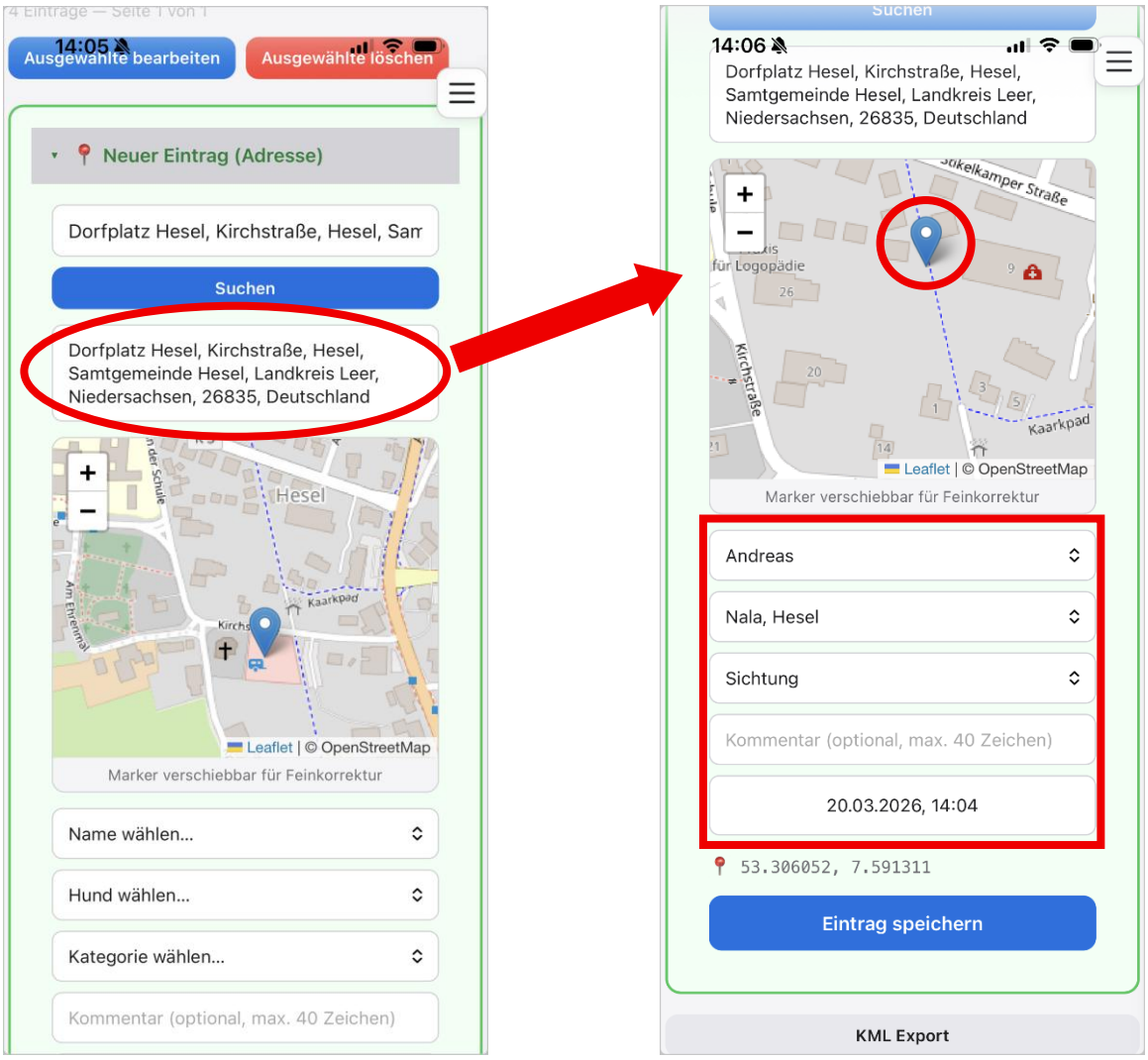

Die Angaben zum Helfer, des Hundes, der Kategorie sowie des Zeitpunkt müssen ebenfalls von Hand angegeben werden.

2.2 Daten Bearbeiten

Bei einem einzeln ausgewählten Datensatz können alle Daten (außer den Koordinaten) geändert werden.

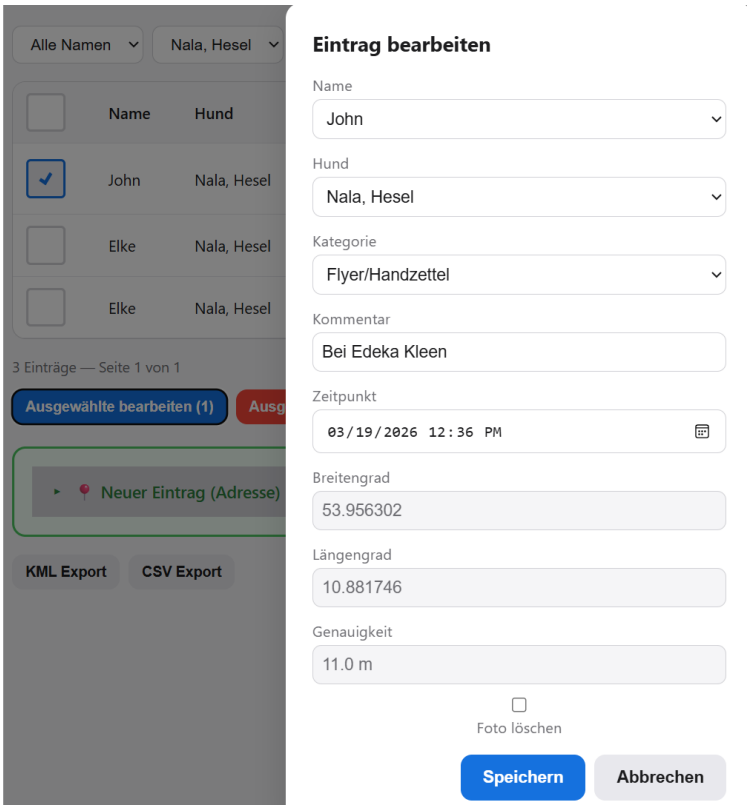

In der Tabelle können mehrere Zeilen markiert und die Daten dort gesammelt geändert werden. Es werden nur die Felder verändert, in welche ein neuer Wert ausgewählt wurde.

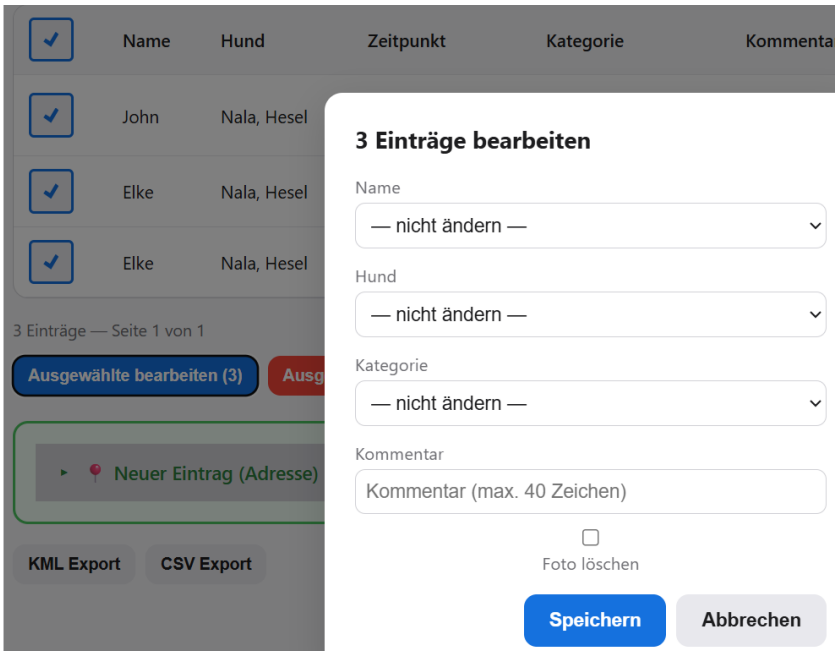

2.3 Kartenansicht

In der Kartenansicht können die gewohnten Filter angewendet werden.

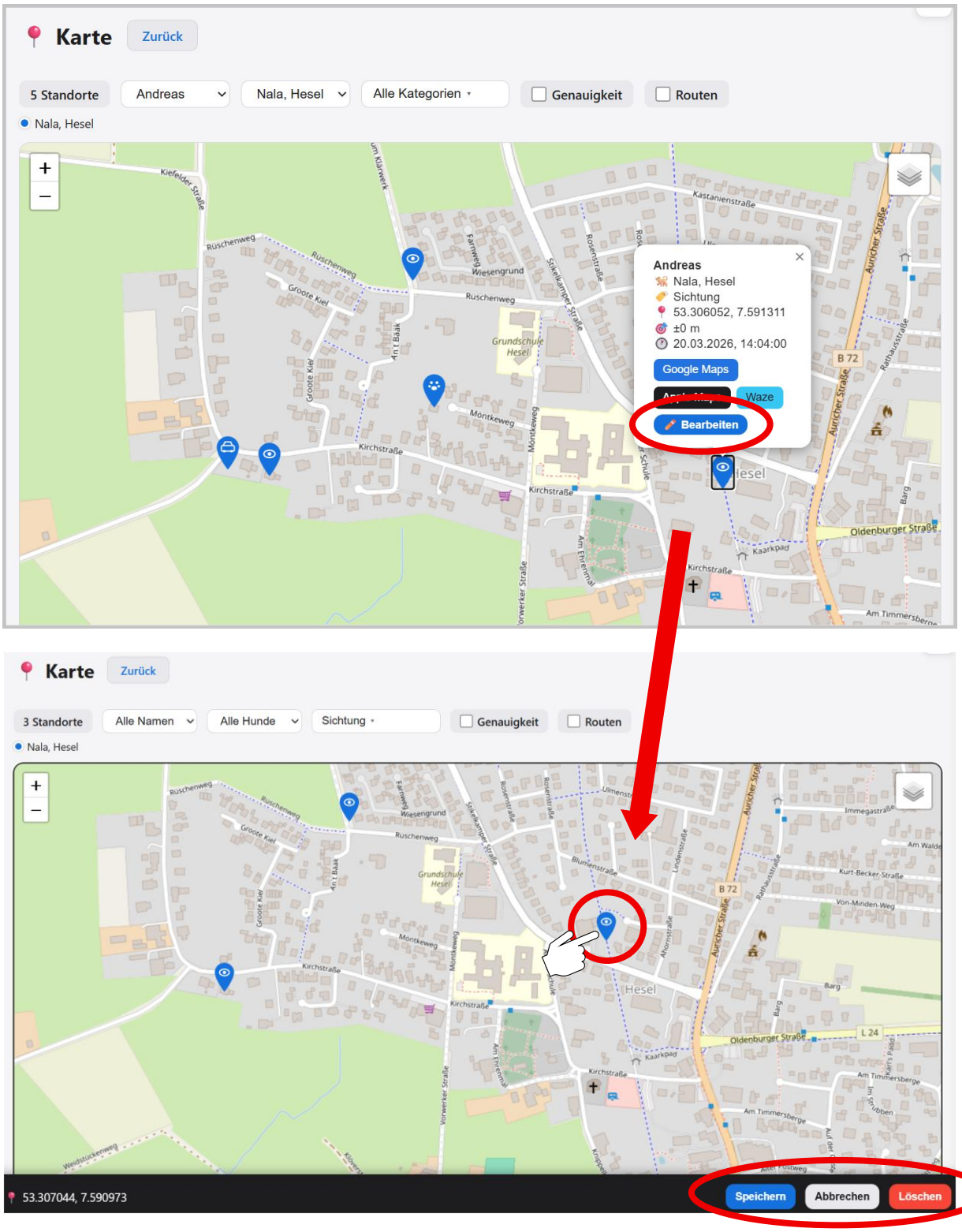

Über die „Bearbeiten“ Funktion können Marker auf der Karte verschoben oder gelöscht werden.

Bei Bedarf kann z.B. der zeitlich Verlauf von Sichtungen als „Route“ abgebildet werden.

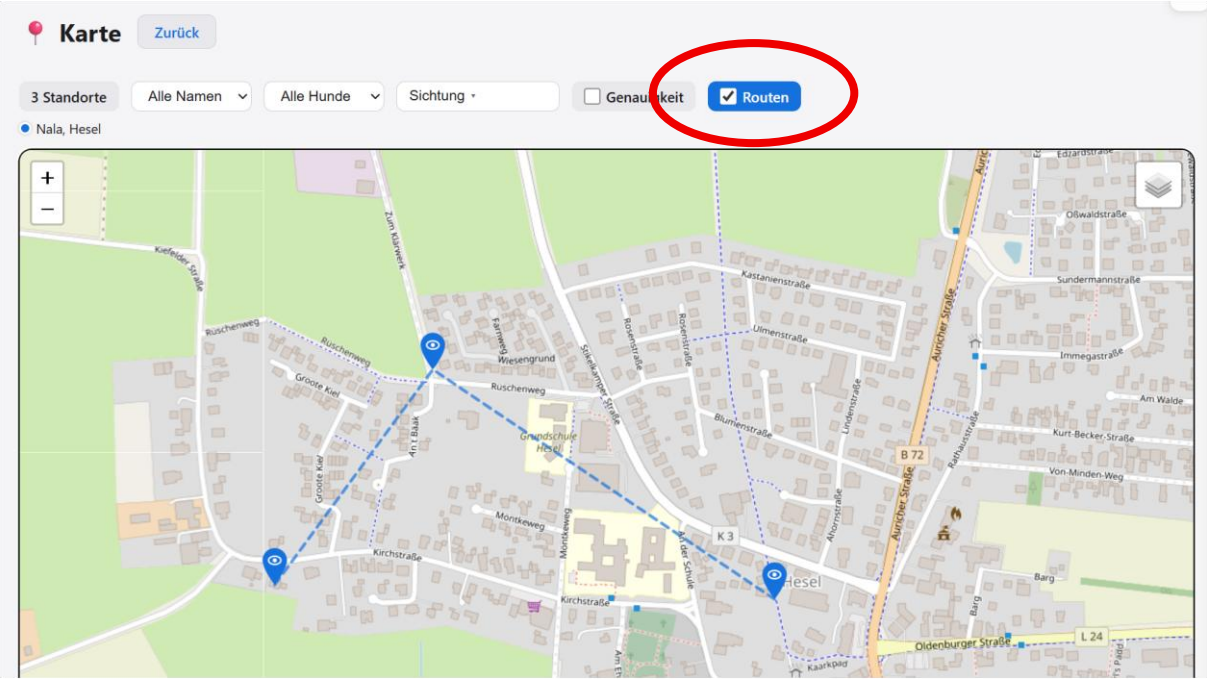

3. Hunde Verwaltung

In diesem Menü können die entlaufenen Hunde angelegt und verwaltet werden. Jeder Hund bekommt einen **eindeutigen Bezeichner**, erstelle aus dem Namen und einer eindeutigen ID. Dieser Bezeichner kann nicht mehr verändert werden. Allerdings kann der **Anzeigenamen jederzeit angepasst** werden.

Bei der Anlage eines neuen Hunde ist es sinnvoll, den Ort mit anzugeben. Dies vereinfacht die Zuordnung bei gleichen oder ähnlichen Hundenamen.

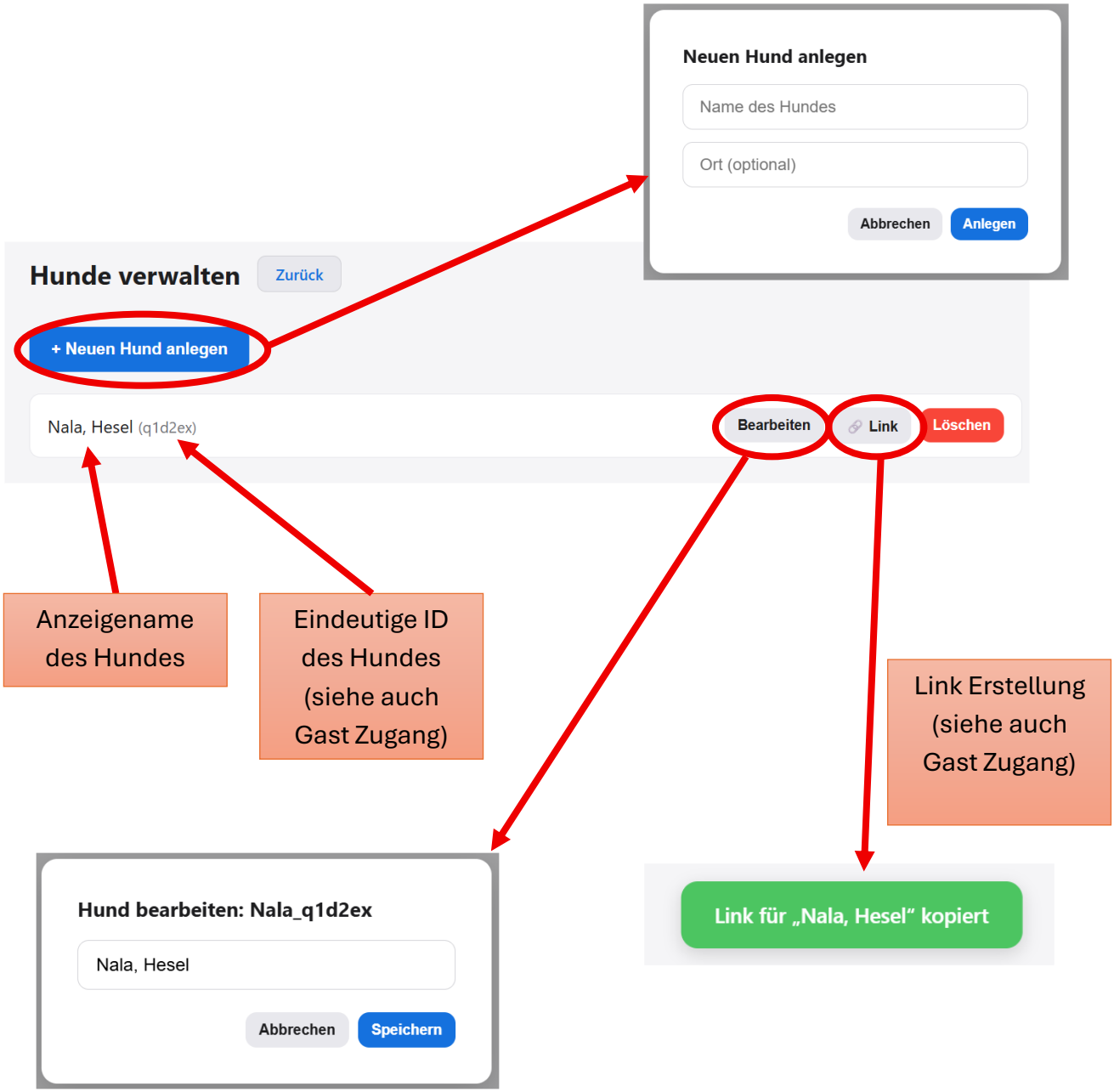

3.1 Gast Zugang

Wenn die Halter des entlaufenen Hundes selbst bei der Fyler Aktion unterstützen möchten, so benötigen sie dafür kein eigenes Benutzerkonto. Der Button „Link“ in der Hundeverwaltung erzeugt einen besonderen Link zu einem eingeschränkten Zugang zur „Erfassung“ neuer Standorte.

Hinweis: Der Link wird automatisch in die Zwischenablage kopiert. Er kann dann ein WhatsApp, einer E-Mail oder dem Browser eingefügt werden.

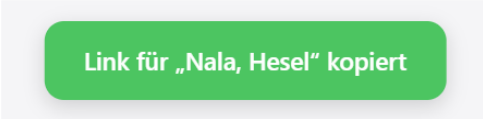

Der Link enthält die eindeutige ID eines jeden Hundes. So ist sichergestellt, dass die Halter auch nur ihren eigenen Hund in der App sehen können.

Beispiel: **https://lostdogtracer.kiefeld.org/guest-home.html?key=q1d2ex**

Darüber hinaus können die Halter ausschließlich Standorte der Kategorie „Flyer/Handzettel“ anlegen und sehen in der Liste bzw. auf der Karte nur ihre eigenen Flyer. Als Benutzername wird in der Tabelle „HALTER*IN“ eingetragen.

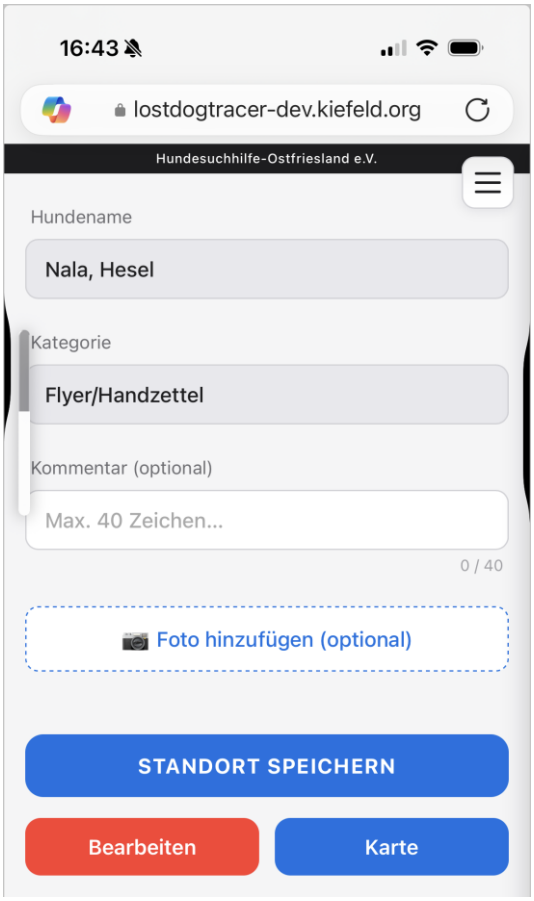

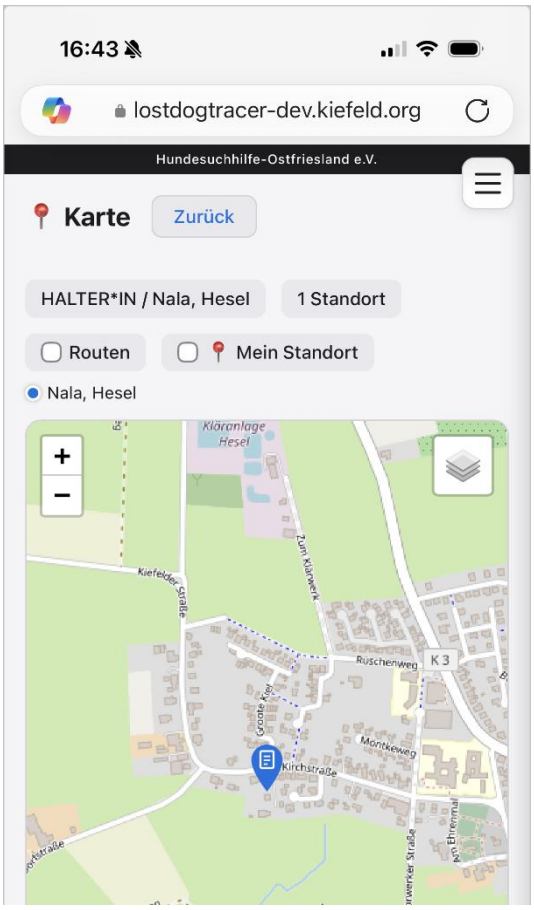

4. Benutzer Verwaltung (eingeschränkt)

In diesem Menü können Manager neue Benutzer anlegen. Dies ist als Unterstützung für die Administratoren gedacht, wenn z.B. kurzfristig ein Helfer eines anderen Verein etc. angelegt werden muss.

In der eingeschränkten Benutzerverwaltung können **nur Benutzer mit der Rolle „User“** angelegt werden. Darüber hinaus sind keine Funktionen enthalten.
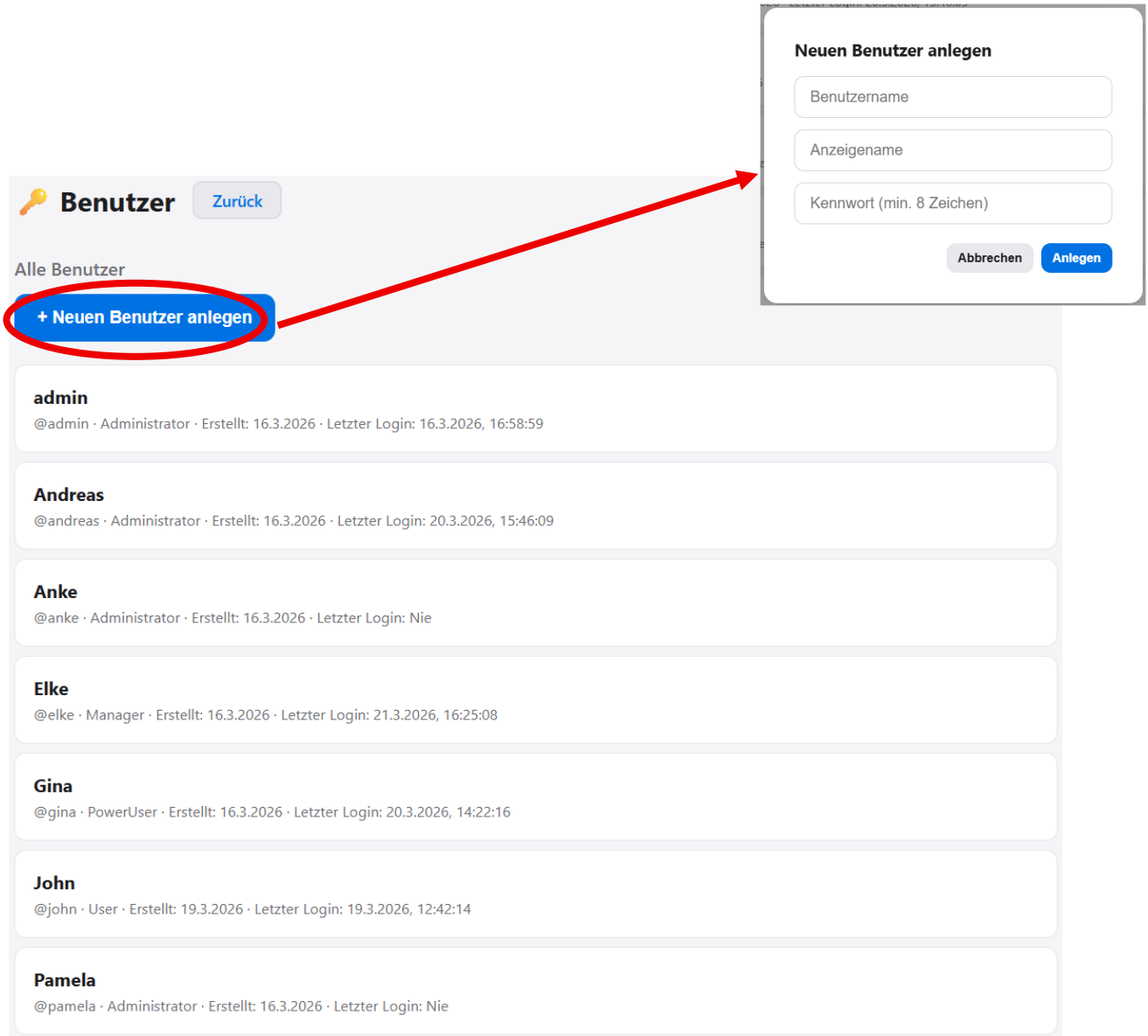
Jeder Benutzer hat einen **eindeutigen Anmeldenamen**. Dieser muss einmalig sein. Doppelte Namen können nicht abgespeichert werde. Der **Anzeigename kann jederzeit geändert** werden (Vom Benutzer selbst oder einem Administrator).